Allende Coahuila

MANUAL DE USUARIO

Jose Gustavo Torres Sotelo

3/4/2026

SIGMU: Sistema Integral de Gestión de reportes Municipales Urbanos

Contenido

Inicio de sesión y Registro 3

Gestión de usuarios, perfil y cambio de contraseña 5

Navegación y comodidad 10

Crear reporte y Ajustes 11

Ver reportes y estadisticas 21

Salir de la sesion 28

Inicio de sesión y Registro



En el inicio de sesión podrás acceder con tu usuario autorizado y activado, desde aquí también puedes entrar a registro para crearte una cuenta

Una vez creado el usuario aparecerá este mensaje

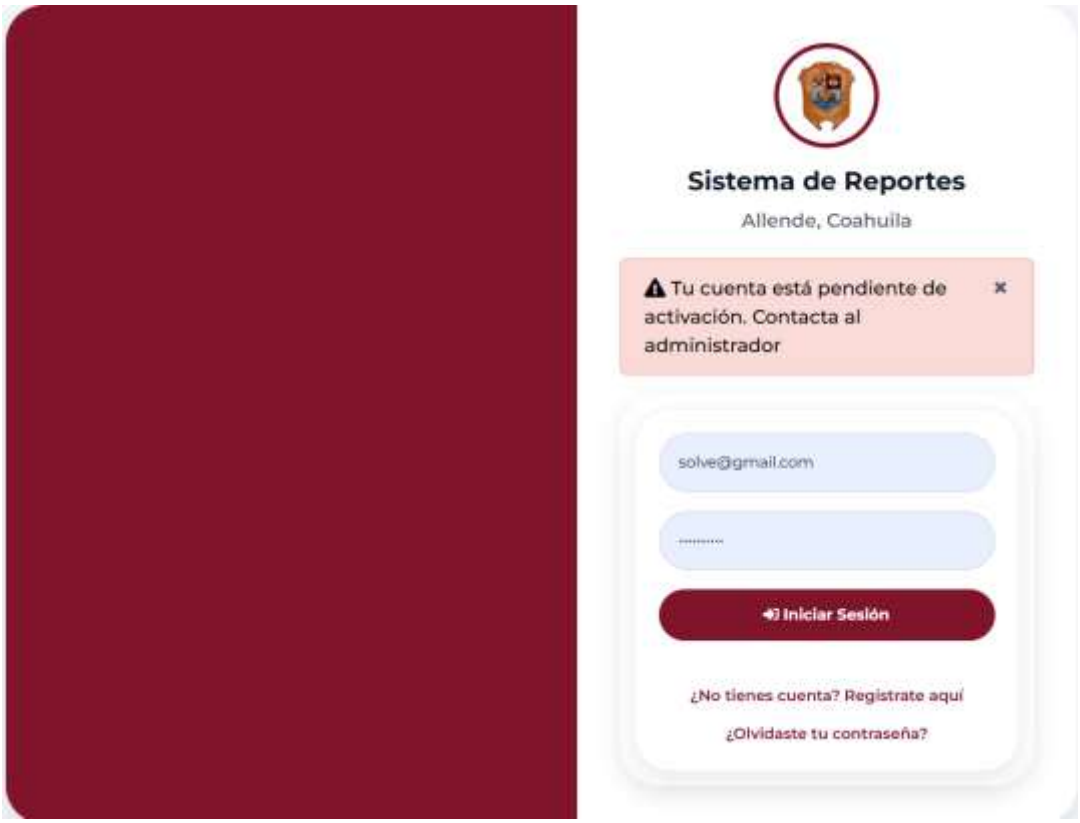

Sin embargo, deberás esperar a que un usuario administrador autorice tu cuenta para poder ingresar. Una vez activada y asignado tu rol, podrás acceder y realizar tus funciones.

Gestión de usuarios, perfil y cambio de contraseña

Para poder acceder a la pagina con todos los privilegios es necesario tener una cuenta de administrador,

En el perfil podremos ver mas detalles sobre el administrador como llegar al perfil bueno tienes que pulsar el icono de usuario desde ahí se abrirá un menú desplegable con tres opciones

- Perfil
- Ajustes
- Cerrar sesión

Nosotros seleccionaremos perfil

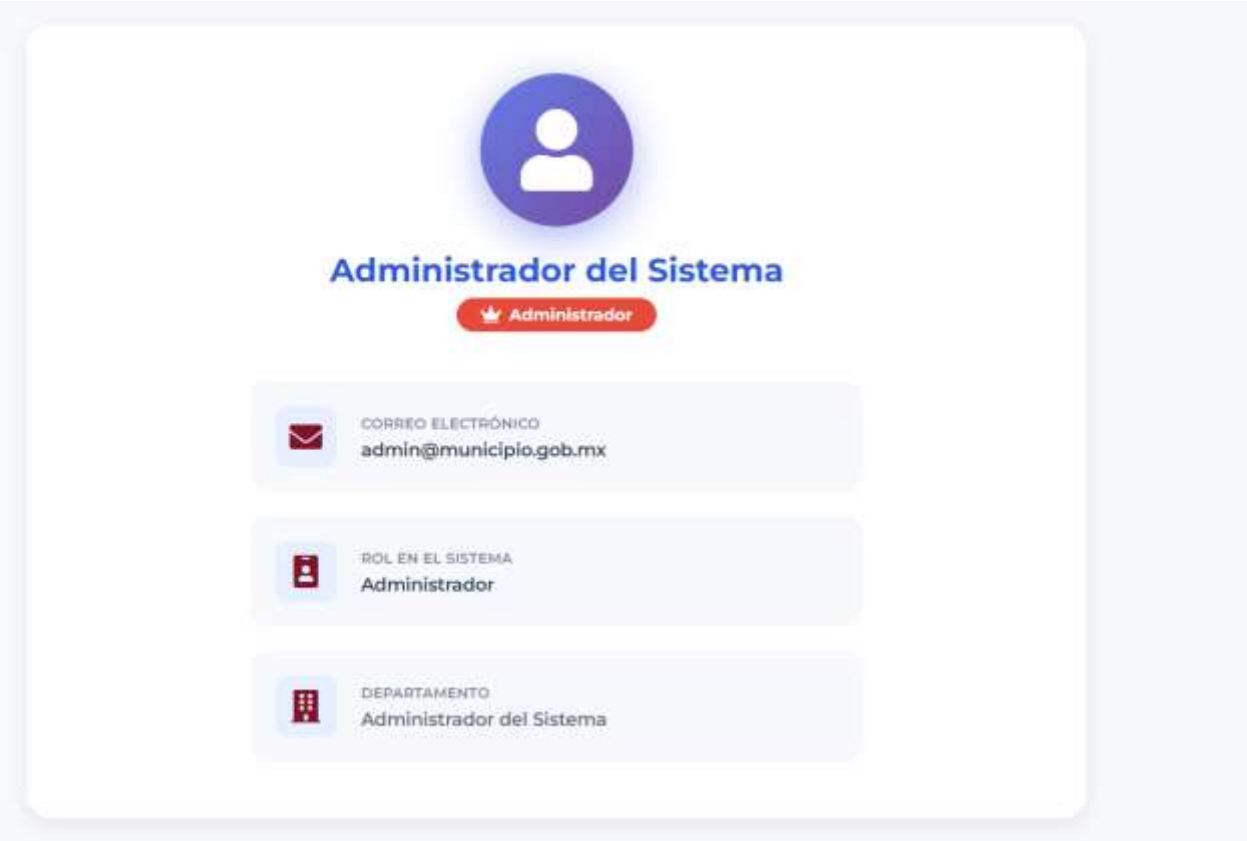

Desde aquí podremos ver todos los atributos de tu usuario en cuestión, después nos iremos a gestión de usuarios

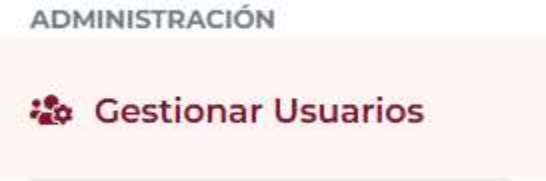

Ahí podremos activar, eliminar o cambiar la contraseña del usuario que así lo requiera

Aquí podemos ver el usuario que creamos anteriormente, como podemos observar aparece toda su información relevante aquí podremos activarlo o rechazarlo, en este caso vamos a activarlo.

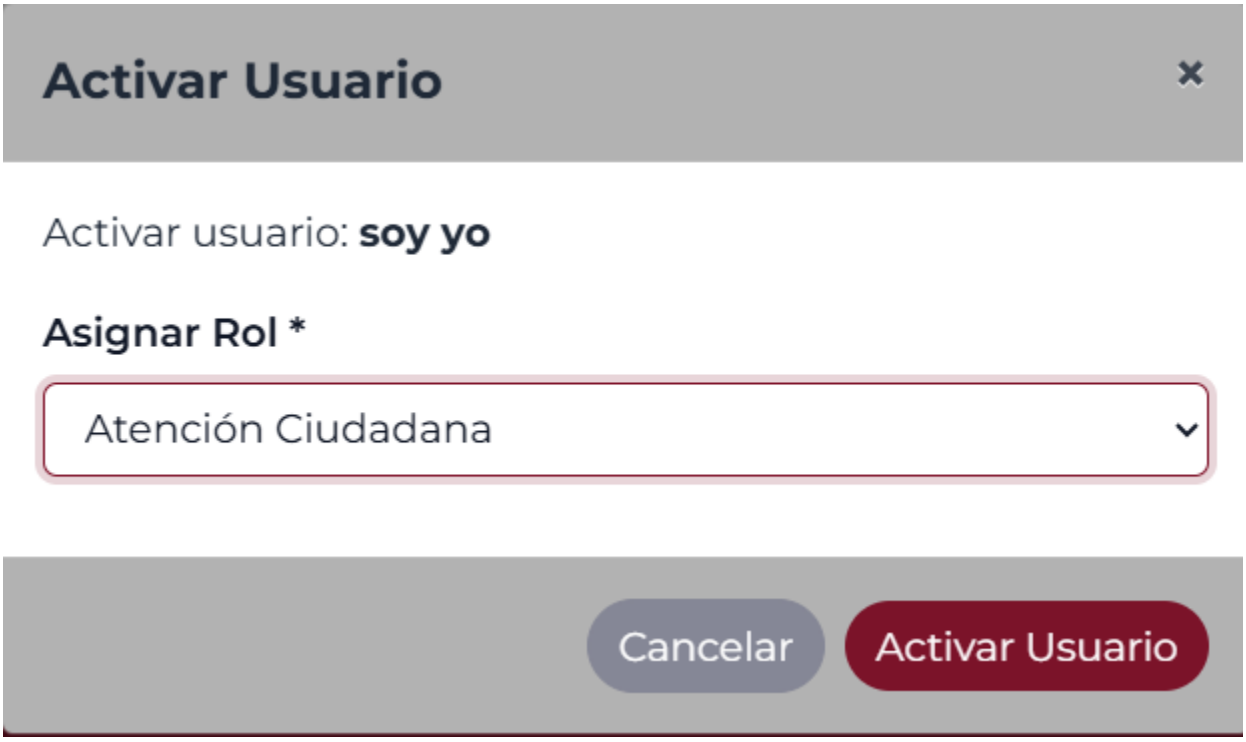

Al intentar activarlo nos aparecerá un cuadro de texto que nos permitirá asignarle un rol a nuestro usuario existen tres el cual seria administrador, departamento y atención ciudadana, primero atención ciudadana solo puede crear reportes los cuales pueden ser de cualquier departamento más sin embargo no puede completarlos, ni modificarlos ni eliminarlos puede ver los reportes de todos los usuarios y puede ver las estadísticas pero no puede modificar nada impidiendo terminar las tareas por sí mismos además tampoco pueden entrar a la gestión de usuarios, en cuanto a los departamentales estos pueden crear eliminar y terminar los reportes correspondientes a su departamento además de ver las estadísticas pero no pueden acceder a la gestión de usuarios y

tampoco tendrán acceso a los reportes de otros departamentos puede ver reportes creados por el administrador o atención ciudadana solo si estos crearon el reporte para dicho departamento, en cuanto el administrador puede crear un reporte de todos los departamentos entrar a estadísticas, completar los reportes y además acceder a la gestión de usuario en nuestro caso para la selección de rol elegiremos administrador.

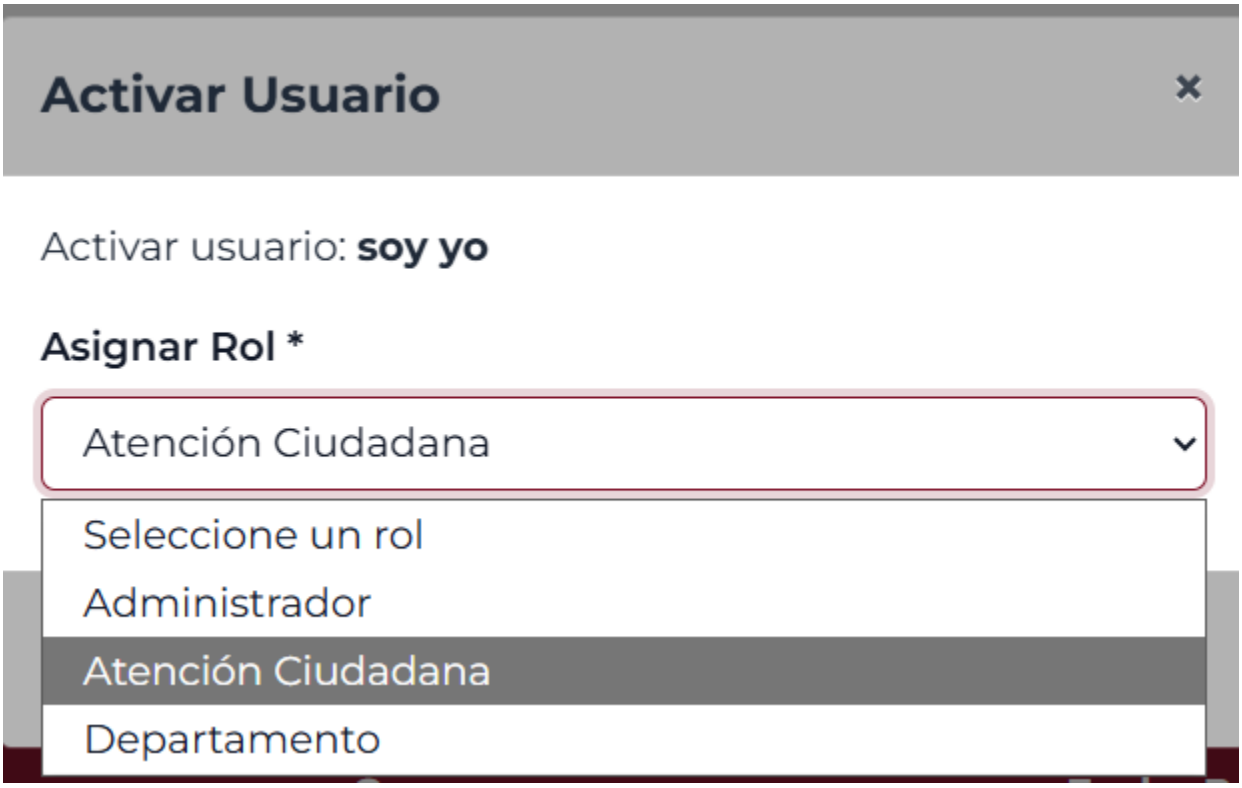

15	usuario	sol1@gmail.com	Departamento	Imagen Urbana	09/03/2026 11:21	Cambiar Depto. Desactivar Eliminar
16	usuario	usuario@municipio.gob.mx	Administrador	-	09/03/2026 11:32	Desactivar Eliminar
17	atencion ciudadana	atencion@municipio.gob.mx	Atención Ciudadana	-	09/03/2026 11:39	Desactivar Eliminar
18	usuario111	usuario111@gob.mx	Administrador	-	11/03/2026 04:45	Desactivar Eliminar
19	asdasdasdasd	solve@gmail.com	Atención Ciudadana	-	23/03/2026 01:15	Desactivar Eliminar
20	soy yo	admin3@municipio.gob.mx	Atención Ciudadana	-	23/03/2026 11:33	Desactivar Eliminar

Mostrando 1 a 14 de 14 registros Anterior 1 Siguiente

En la tabla de abajo se enumera los usuarios que actualmente están activos desde aquí se pueden desactivar, eliminar o cambiar el departamento.

Navegación y comodidad

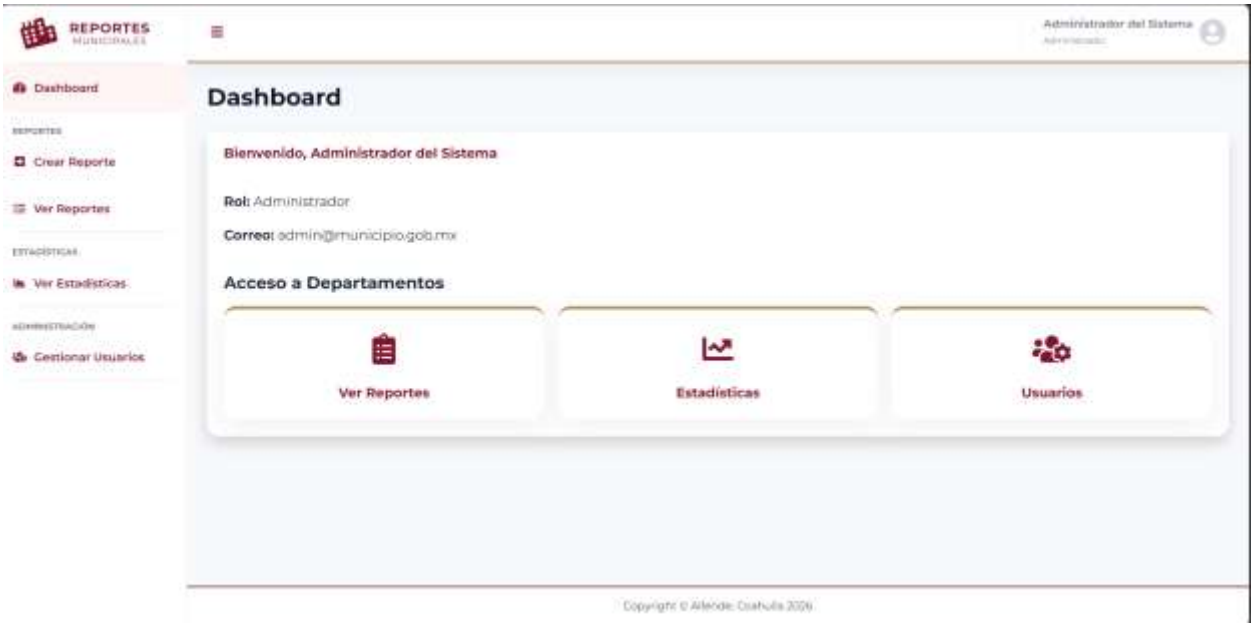

En la pagina podremos navegar a donde queramos si somos administradores en caso de no serlo solo se bloquearía gestión de usuario. Pero venimos a revisar el menú de alado en donde dice reportes municipales en ese menú están las opciones de Dashboard, crear reporte, ver reportes, ver estadísticas y gestión de usuarios siendo casi enteramente la pagina en caso de estar trabajando en una sola pestaña podremos darle al botón de hamburguesa superior.

Para quitar el menú lateral

Crear reporte y Ajustes

En la creación de reporte debernos de llenar campos como lo son nombre, teléfono, método de contacto y descripcion del problema en selección del departamento solo estará disponible para atención ciudadana y administrador.

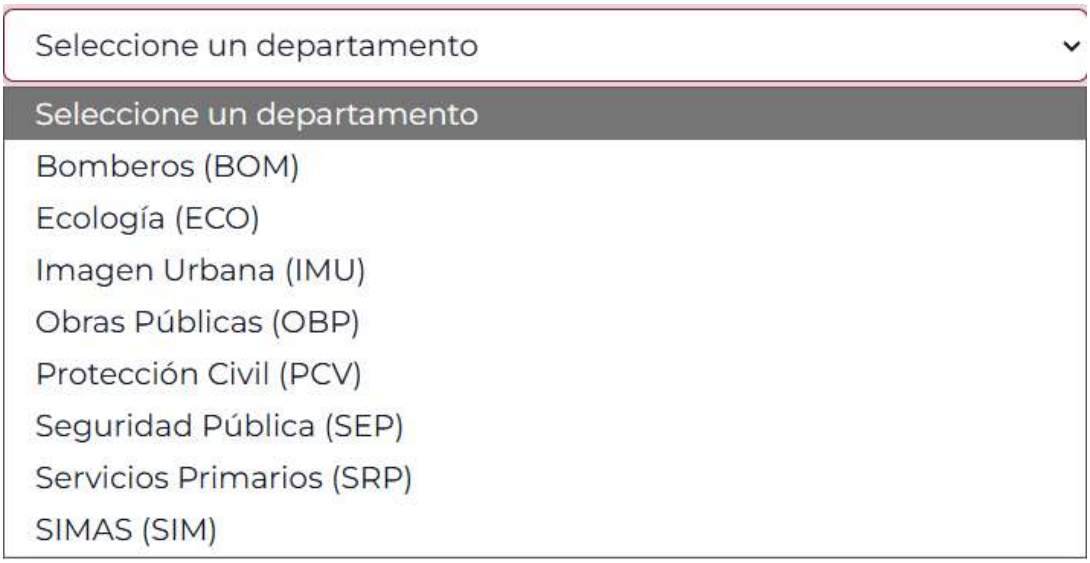

En forma de contacto podremos seleccionar la manera en la que se nos contactó en donde hay tres opciones en personal, llamada y WhatsApp seleccionaremos porque medio se nos informó. En caso de la ubicación compartida podremos seleccionar coordenadas de Google para encontrar la ubicación necesaria la forma de contacto. Primero entramos a Google Maps, segundo seleccionamos una ubicación que en este caso sería la ubicación del ciudadano.

Seleccione una opción

Seleccione una opción

En persona

Llamada

WhatsApp

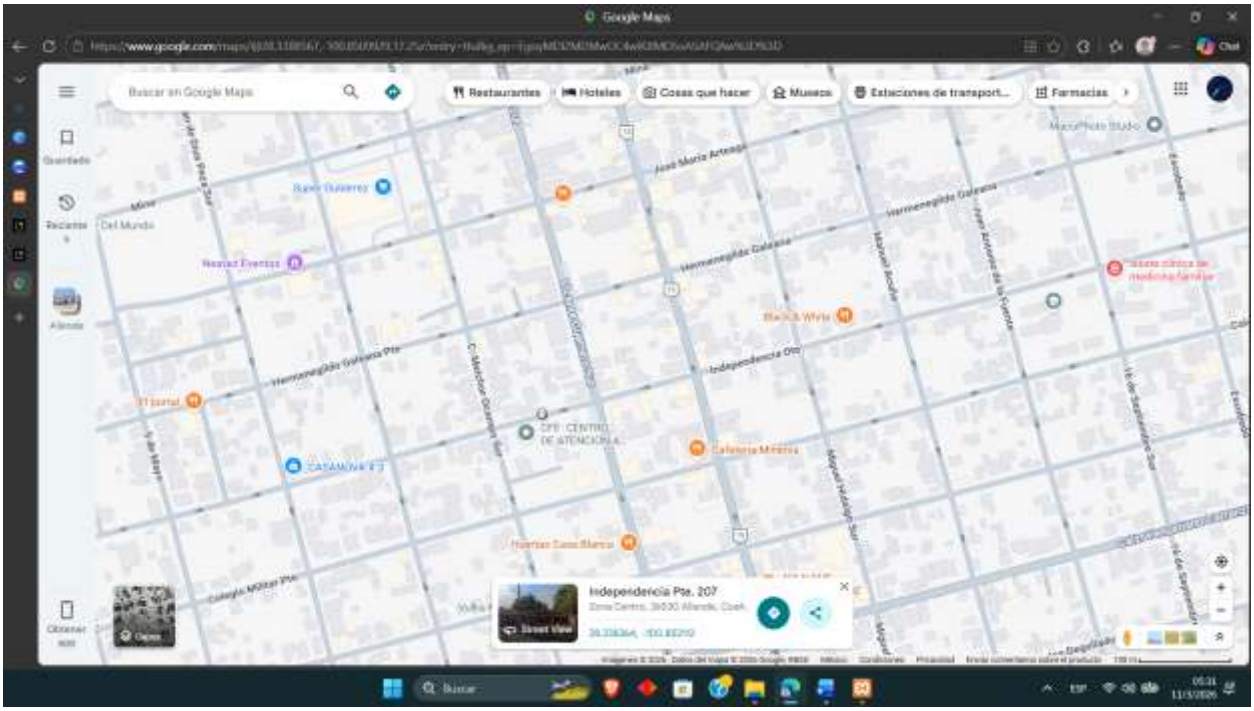

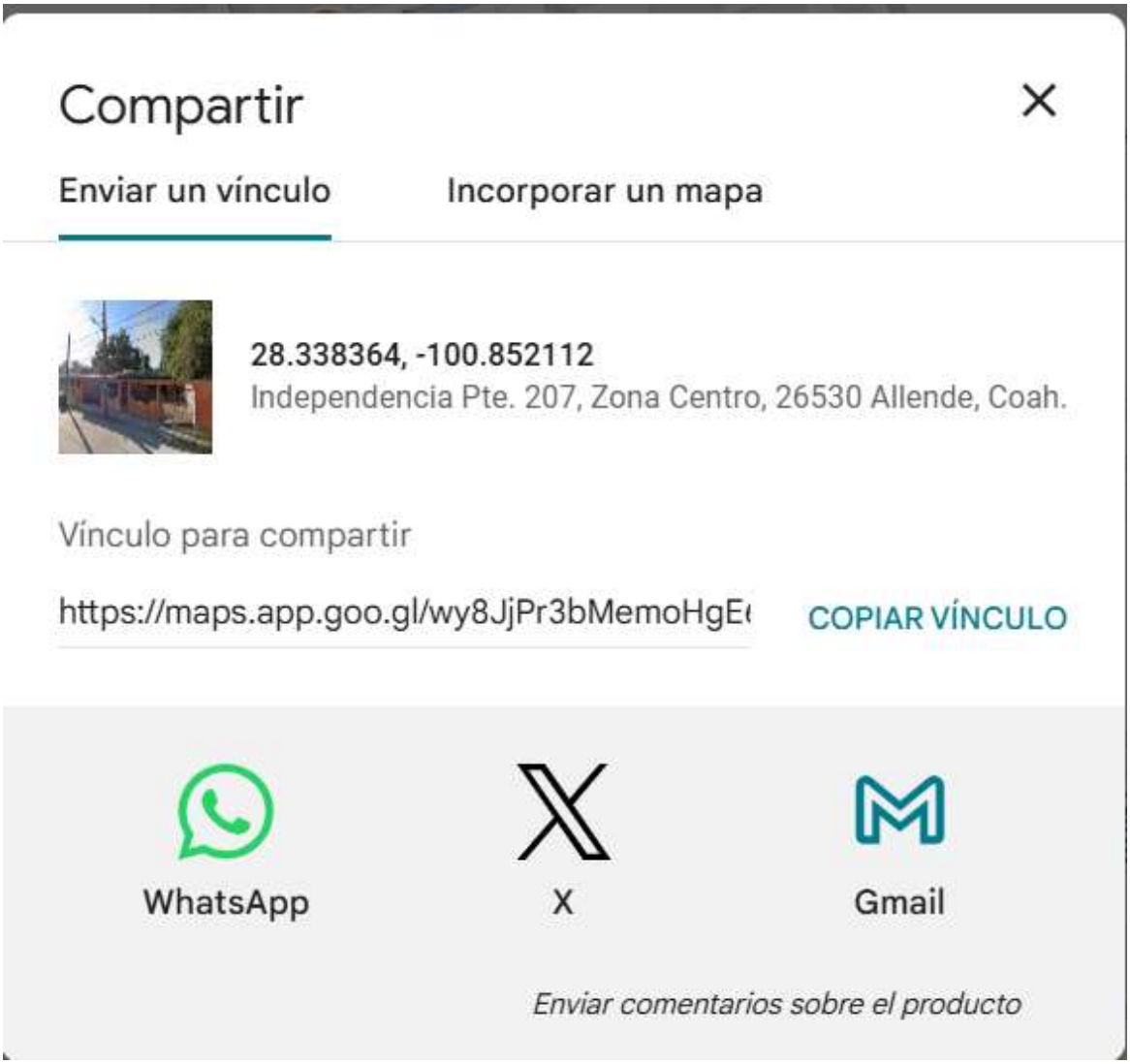

tercero copiamos las coordenadas.

Copiamos las coordenadas de arriba 28.344576, -100.848098 y por último vamos a la página y activamos la ubicación copiamos esas coordenadas en ubicación compartida y le damos importar

Una vez hecho eso tendremos la ubicación compartida del ciudadano en caso de no saber en donde reside el ciudadano y que el ciudadano no sepa dar la dirección se puede buscar la calle de esta manera.

Buscaremos por ejemplo la calle guerrero y aparecerán los resultados próximos

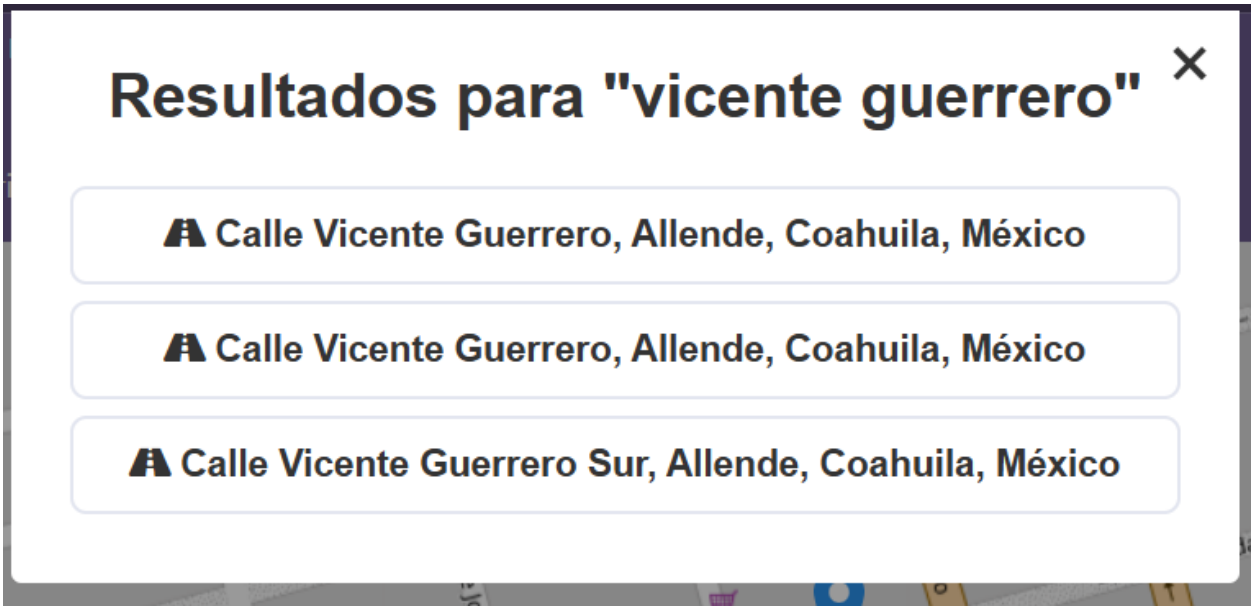

La posición de la calle puede variar mas sin embargo esto te permitirá orientarte

En el caso de que conozcas la ubicación puedes directamente seleccionar una ubicación en el mapa puesto que el mapa es interactivo al pulsar en un lugar del mapa automáticamente te devolverá las calles correspondientes más sin embargo el mapa puede falla o lazar resultados erróneos es bastante raro que pase, pero no imposible así que lo mejor es estar atento y revisar que las calles sean correctas.

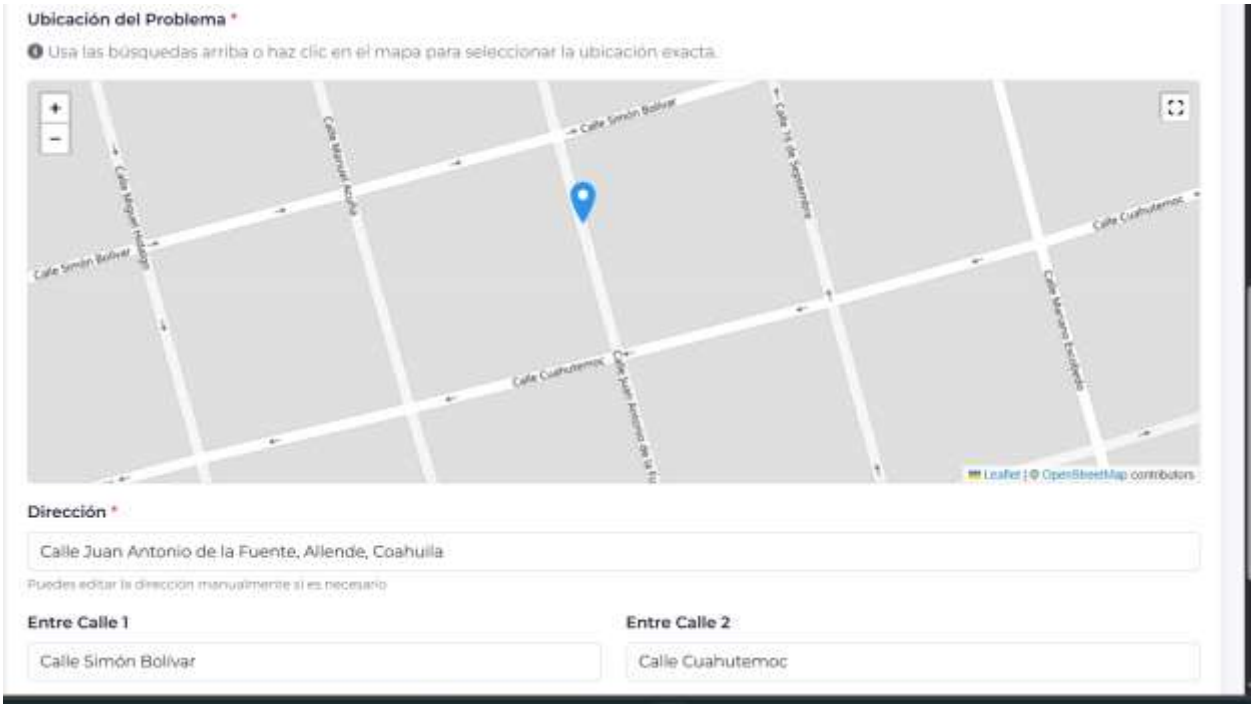

Además, que el mapa también tiene botones uno es para reducir e incrementar la distancia del mapa básicamente es un zoom in zoom out, además de hacerlo grande

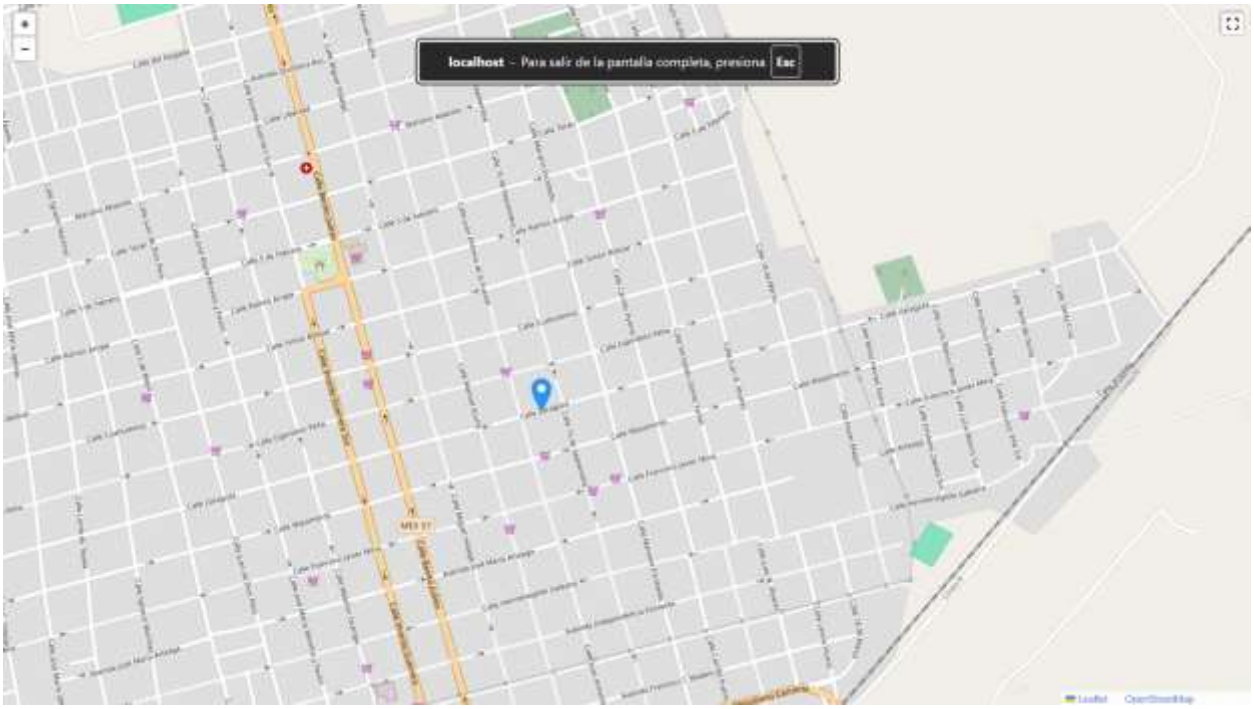

Por ultimo la pagina nos permite subir una imagen al reporte en caso de tenerlo, pero esta es opcional

En caso de tener reportes anteriores a la fecha del sistema podremos ir a ajustes y activar esta pestaña

Una vez habilitado podremos seleccionar la fecha de inicio y cual seria el estado del reporte en caso de seleccionar que el reporte esta completado la pagina añadira dos nuevos campos que tambien deberan ser llenados los cuales son fecha y hora de terminacion y observaciones del departamento.

Fecha del Reporte

23/03/2026

Selecciona la fecha en que ocurrió el problema (no puede ser futura)

Estado del Reporte *

En Proceso

Selecciona "Completado" si el problema ya fue resuelto

Fecha del Reporte

23/03/2026

Selecciona la fecha en que ocurrió el problema (no puede ser futura)

Fecha y Hora de Terminación

dd/mm/aaaa --:--

Opcional. Si no se especifica, se usará la fecha y hora actual del sistema

Estado del Reporte *

Completado

Selecciona "Completado" si el problema ya fue resuelto

Reporte Completado: Proporciona las observaciones sobre cómo se resolvió el problema.

Observaciones del Departamento *

Describe cómo se resolvió el problema

Obligatorio para reportes completados

una ves completado todos los campos podremos darle al boton de registrar

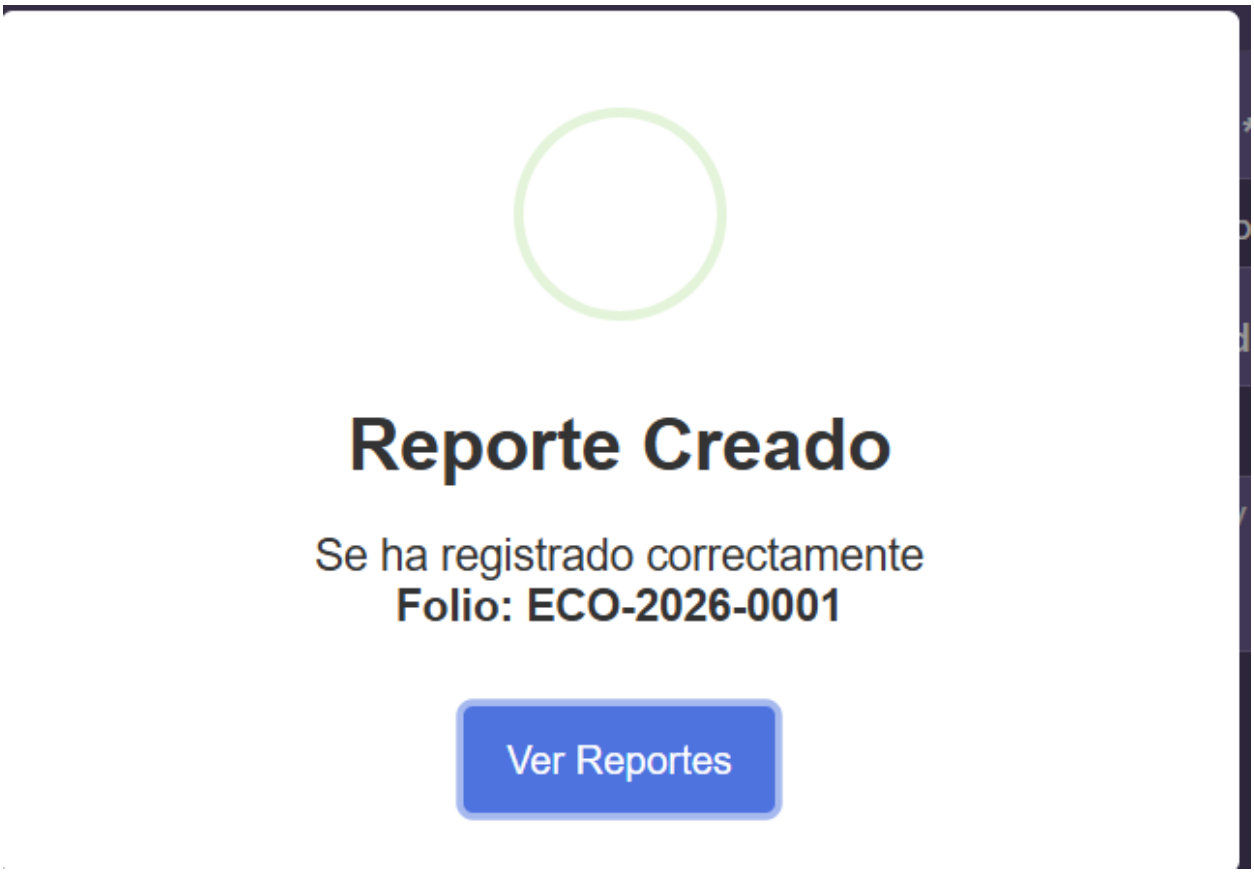

Ver reportes y estadisticas

En la pestaña de ver reportes podremos ver los reportes que estan registrados en la pagina

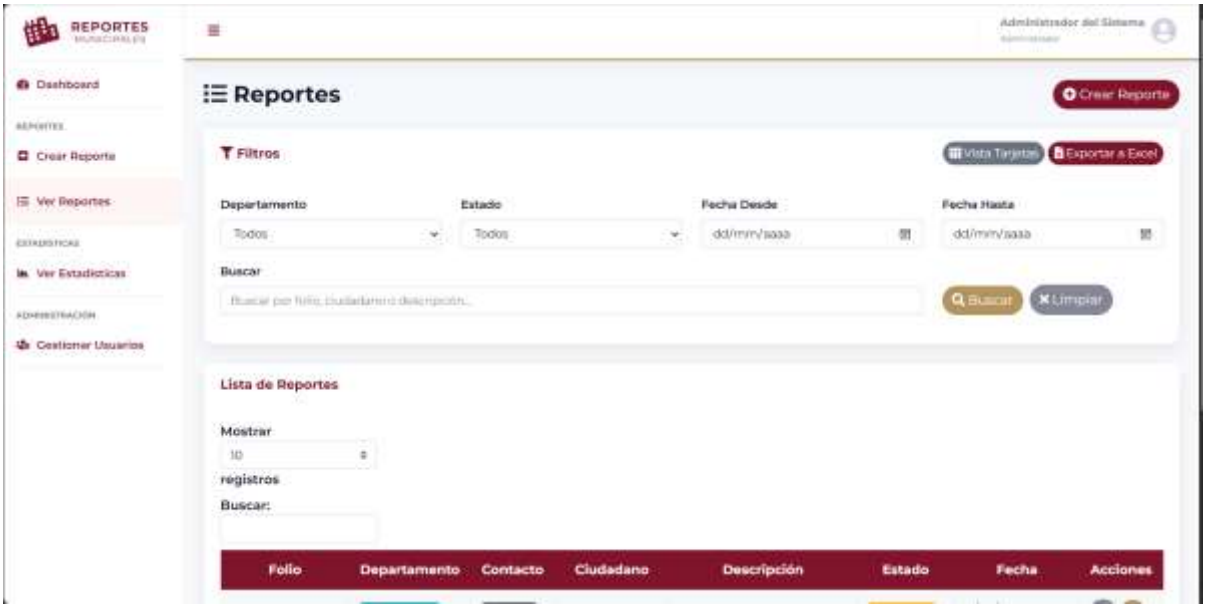

Asi como tambien podremos ver el filtro seleccionar una vista previa por targetas o exportar a excel

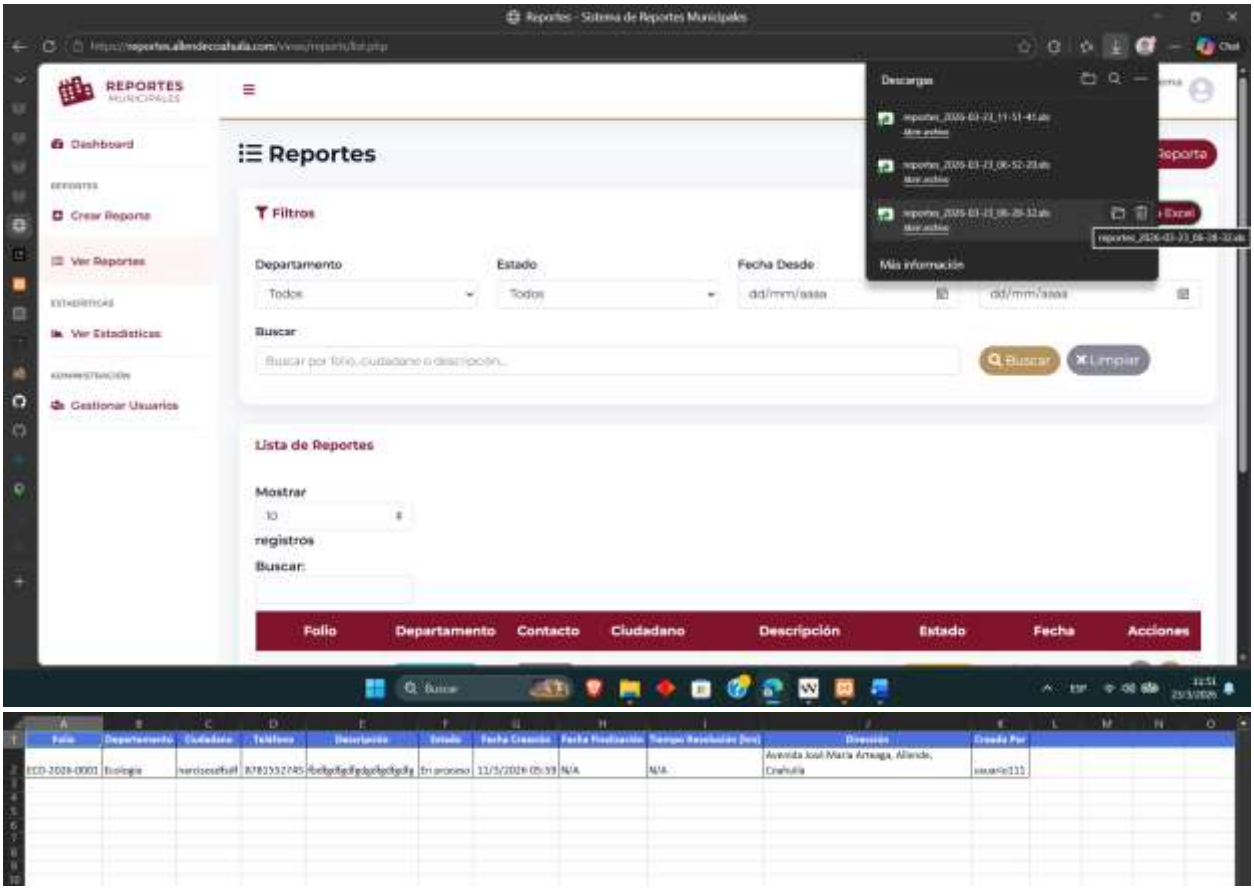

Dentro de los detalles de un reporte podremos ver la informacion importante del reporte

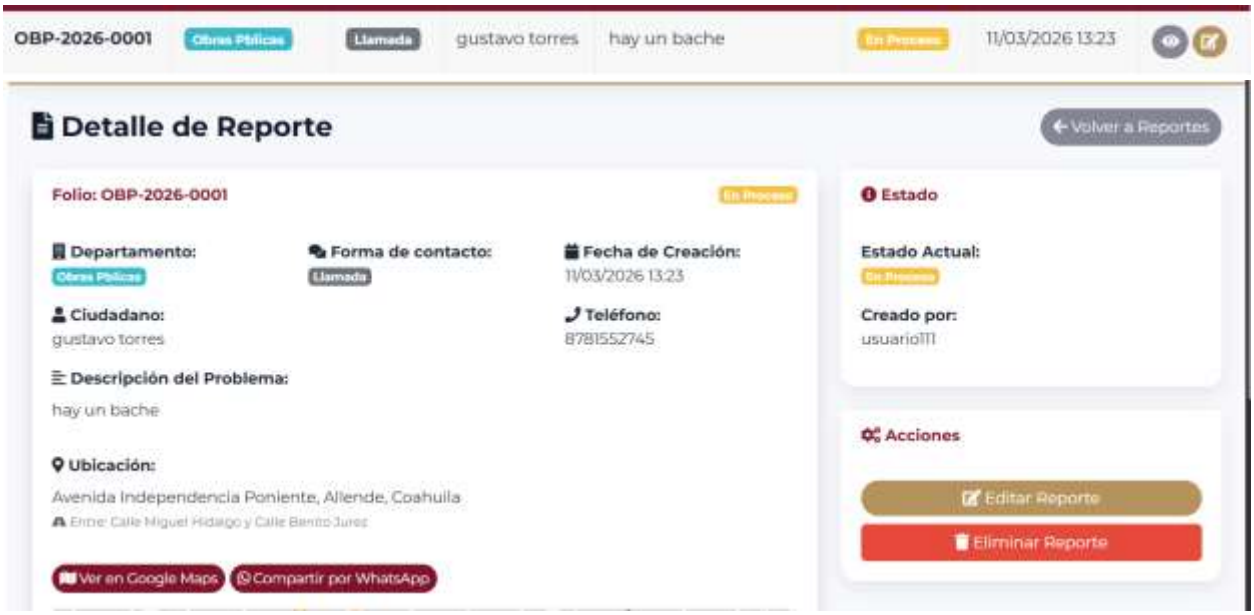

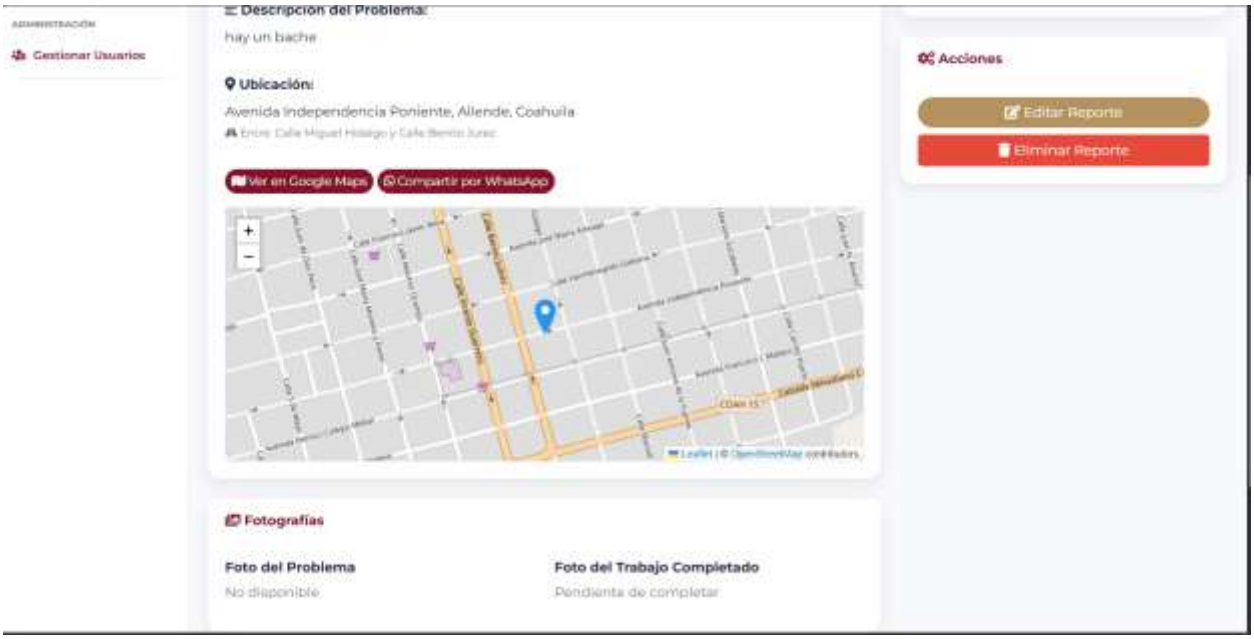
ADMINISTRACIÓN
Gestionar Usuarios
Descripción del Problema:
hay un bache
Ubicación:
Avenida Independencia Poniente, Allende, Coahuila
Entre Calle Miguel Hidalgo y Calle Benito Juárez
Ver en Google Maps
Compartir por WhatsApp
Leaflet | © OpenStreetMap contributors
Fotografías
Foto del Problema
No disponible
Foto del Trabajo Completado
Pendiente de completar
Acciones
Editar Reporte
Eliminar Reporte

Historial de Cambios
Fecha
Usuario
Cambio
Observaciones
11/03/2026 13:23
usuario111
En proceso
Reporte creado

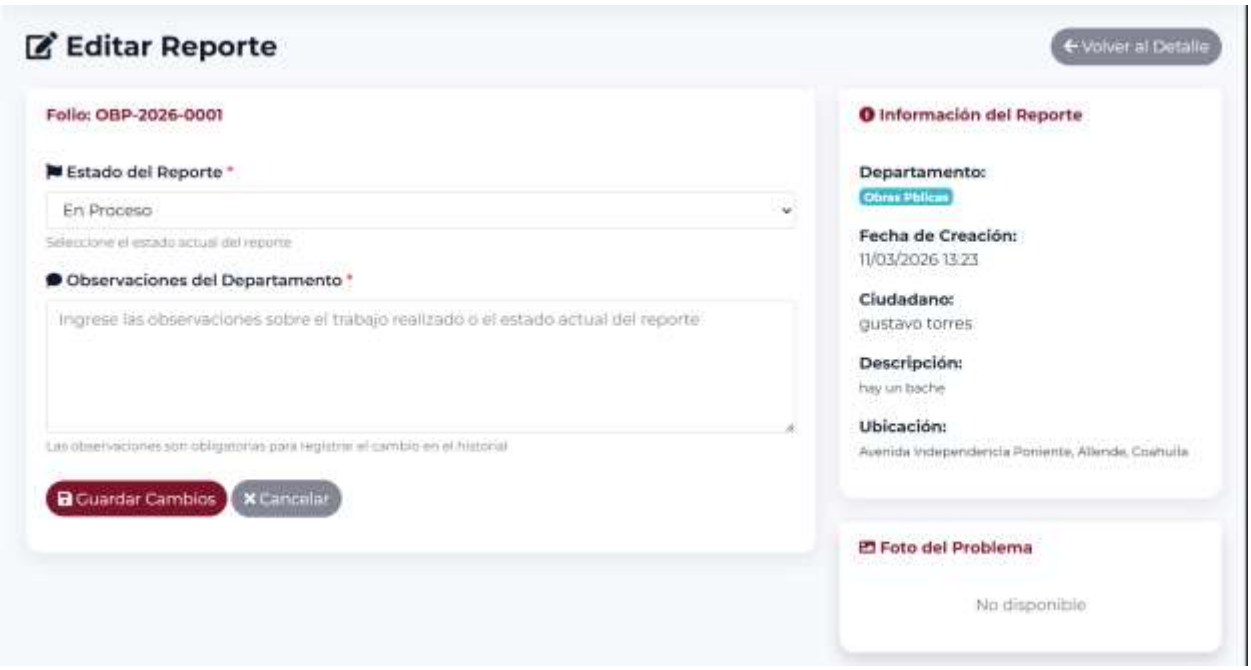
Editar Reporte
Volver al Detalle
Folio: OBP-2026-0001
Estado del Reporte *
En Proceso
Seleccione el estado actual del reporte
Observaciones del Departamento *
Ingrese las observaciones sobre el trabajo realizado o el estado actual del reporte
Las observaciones son obligatorias para registrar el cambio en el historial
Guardar Cambios
Cancelar
Información del Reporte
Departamento:
Obras Públicas
Fecha de Creación:
11/03/2026 13:23
Ciudadano:
gustavo torres
Descripción:
hay un bache
Ubicación:
Avenida Independencia Poniente, Allende, Coahuila
Foto del Problema
No disponible

En el reporte podremos ver diversas cosas ademas de la informacion relevente que nos dice quien lo creo y ademas quien lo reporto tambien, nos permite enviar la ubicación por whatsApp y ademas verla en google maps.

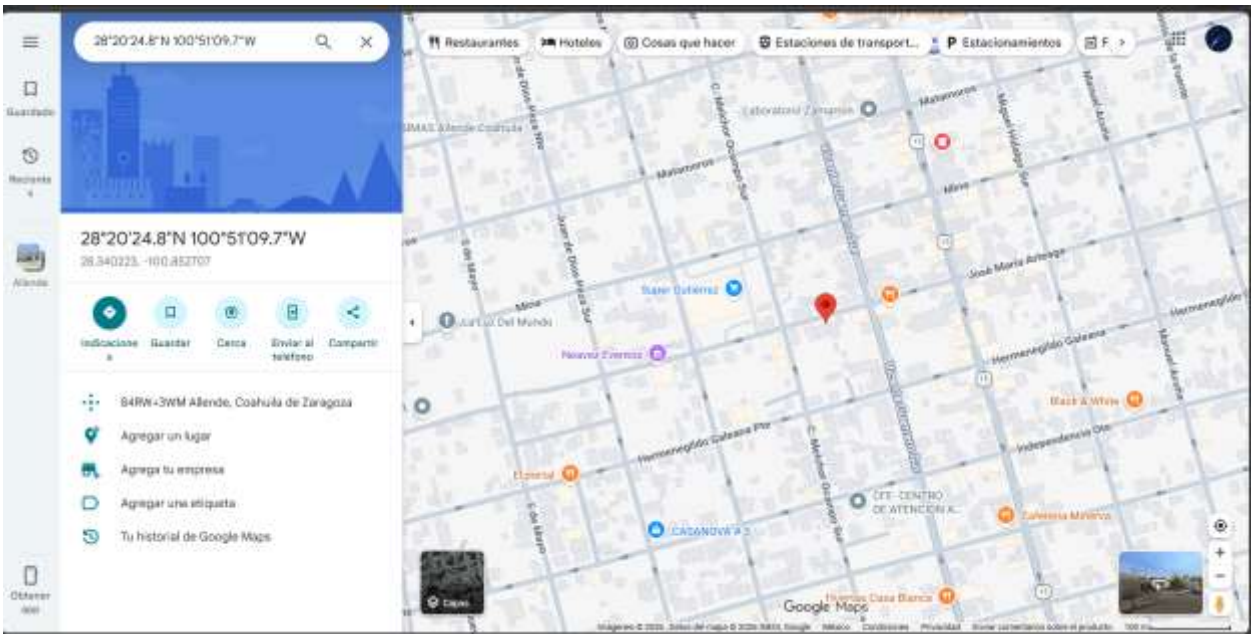

ahí podremos enviar el mensaje a quien queramos.

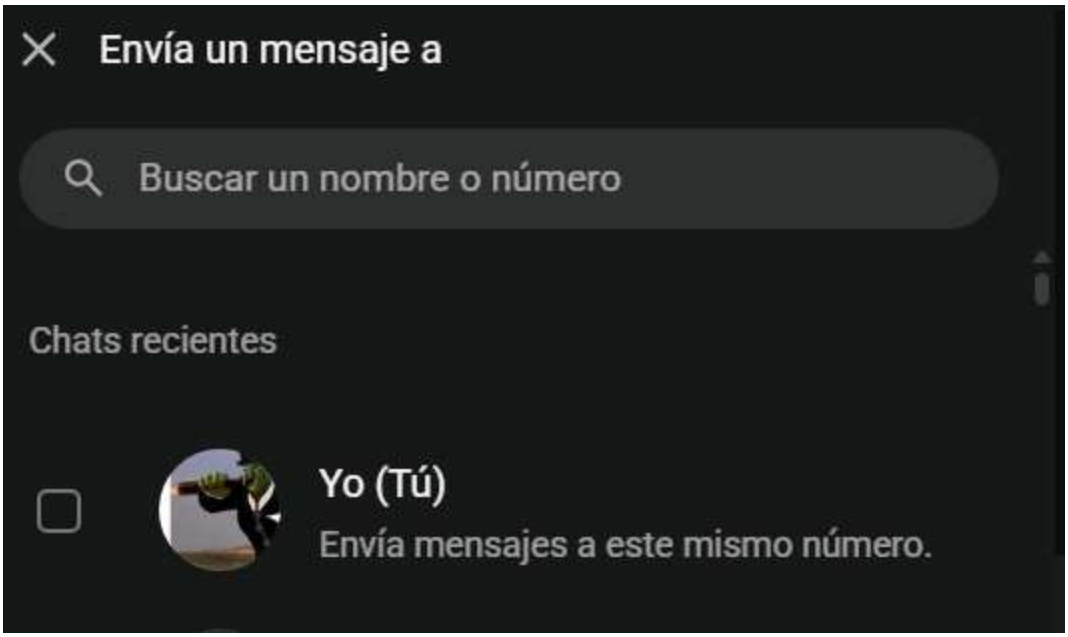

Y nos mandara el reporte.

Esto esta pensado para que los usuarios se lo manden a los trabajadores que se encargan de reparar o solucionar los problemas que esten descritos en los reportes.

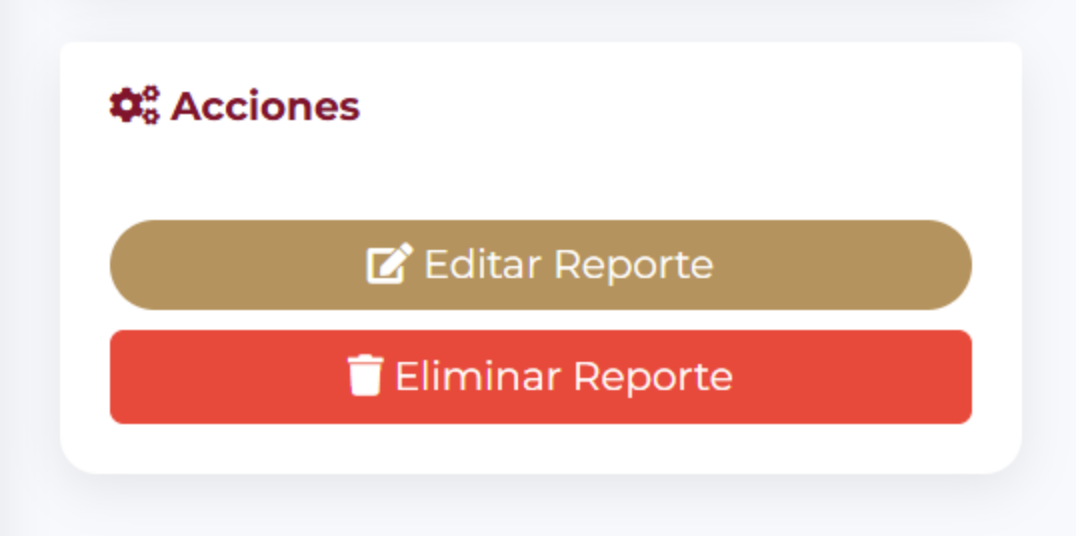

Aquí podremos editar o eliminar reportes si lo eliminamos el reporte se desechara pero si decidimos editarlo podremos seleccionar que queremos hacer con el como dejarlo para que siga en proceso poniendo una observacion departamental o completarlo.

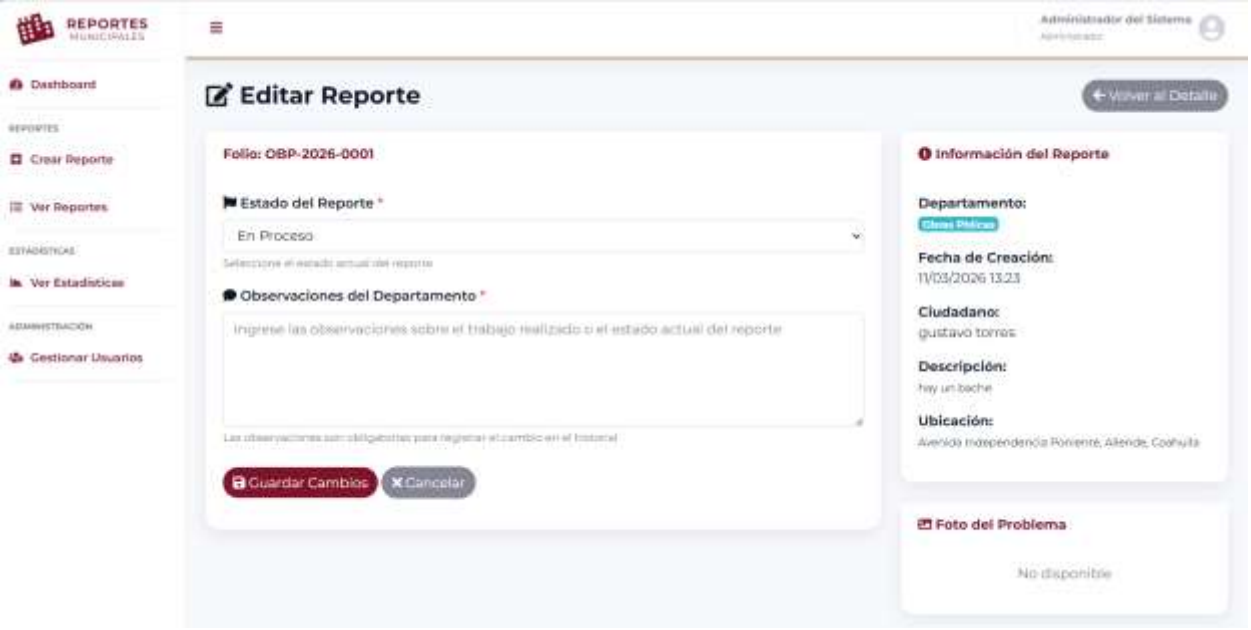

Si decidimos completarlo podremos seleccionar una imagen que es opcional

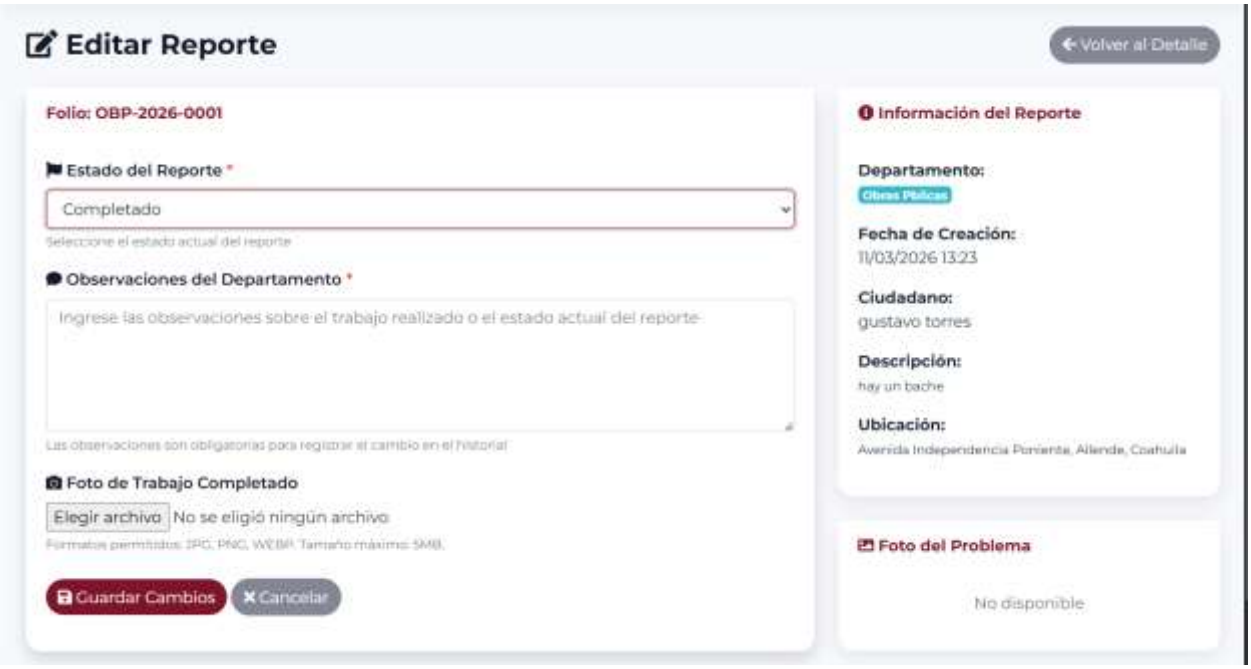

Una vez todo este en orden solo quedaría en guardar cambios y el reporte quedaria terminado

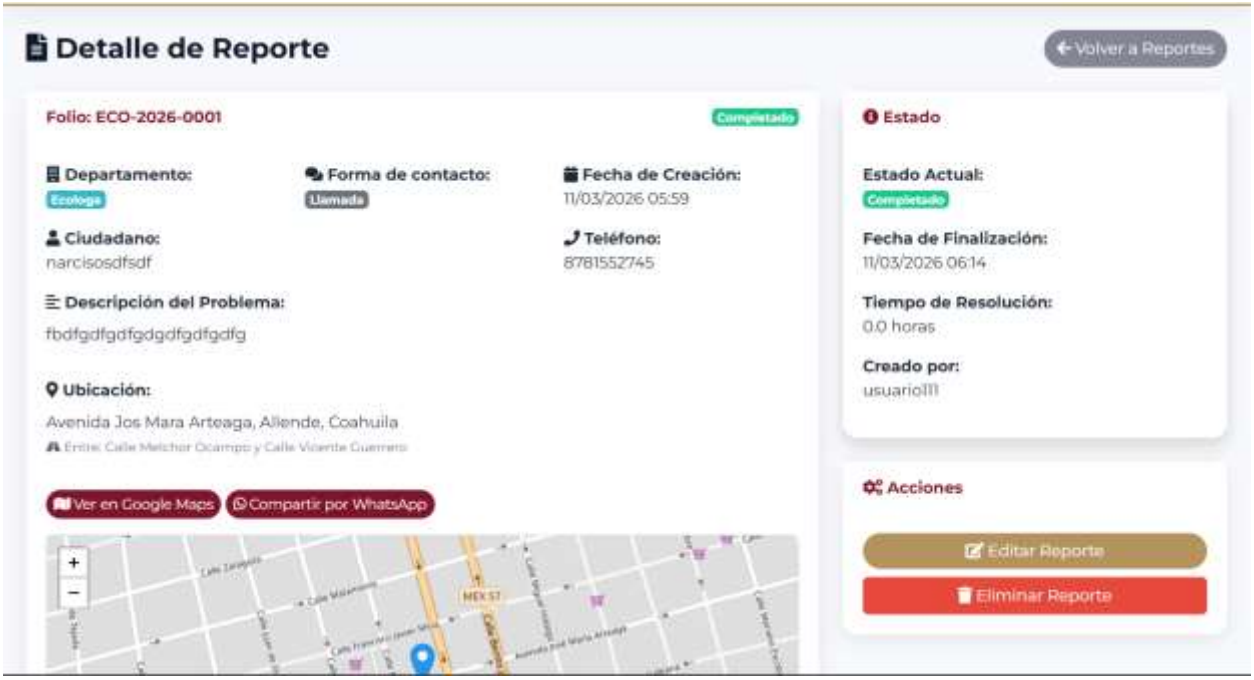

Salir de la sesion

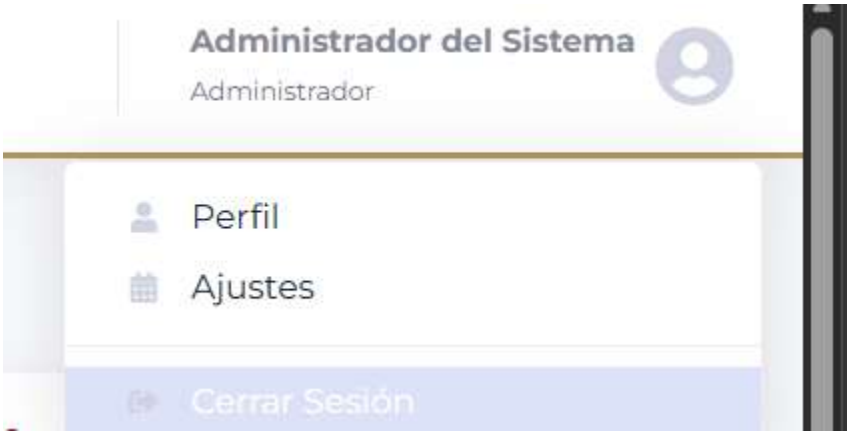

Por último, solo le daremos en cerrar sesión para volver al inicio de sesión